BOLETÍN DE MONITOREO HIDROMETEOROLÓGICO - ESMERALDAS
Proyecto AdaptaClima / INAMHI

Fecha y hora de emisión: Jueves 12 de marzo de 2026, 11:00

La **Dirección de Pronósticos Y Alertas Hidrometeorológicas del INAMHI**, con base en la información registrada en la Estación Hidrológica **San Mateo (H5033)**, la **Estación Meteorológica Automática (EMA) Quinindé (M0156)** del INAMHI, y la **Estación Meteorológica Convencional (EMC) Tachina - Esmeraldas (84018)** de la Dirección General de Aviación Civil (DGAC), así como en los resultados del **modelo numérico WRF**, emite el siguiente Boletín de Monitoreo Hidrometeorológico para la provincia de Esmeraldas.

Vigilancia De Condiciones Hidrológicas

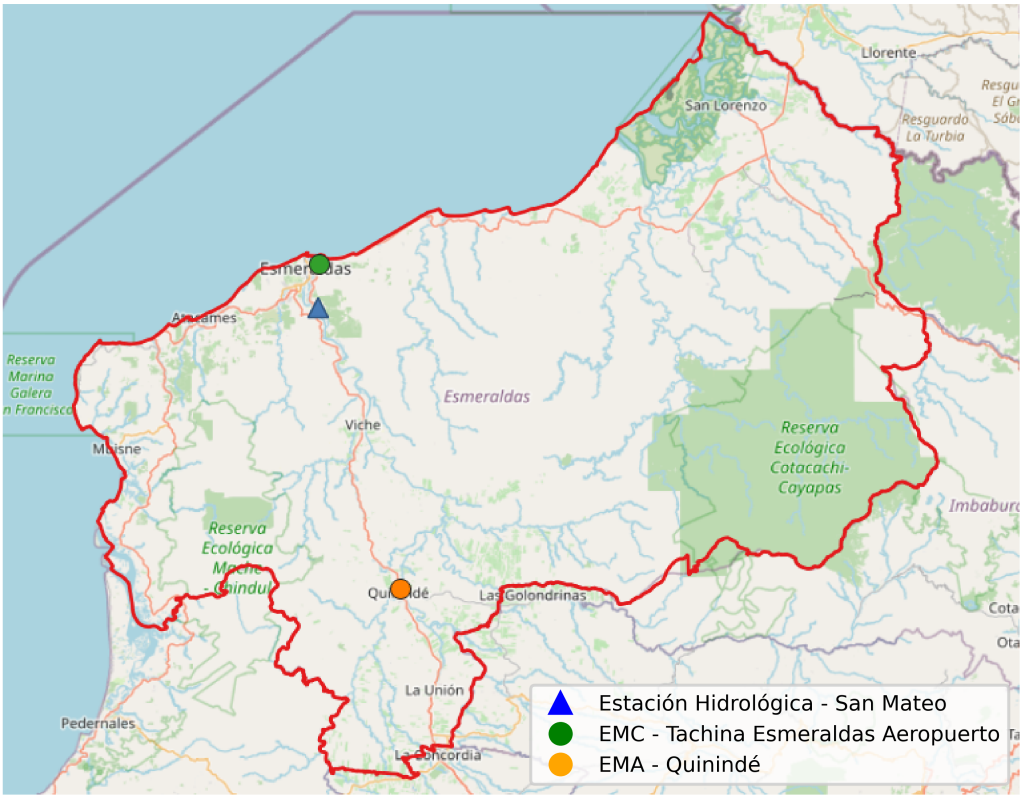

Monitoreo hidrológico – Estación San Mateo

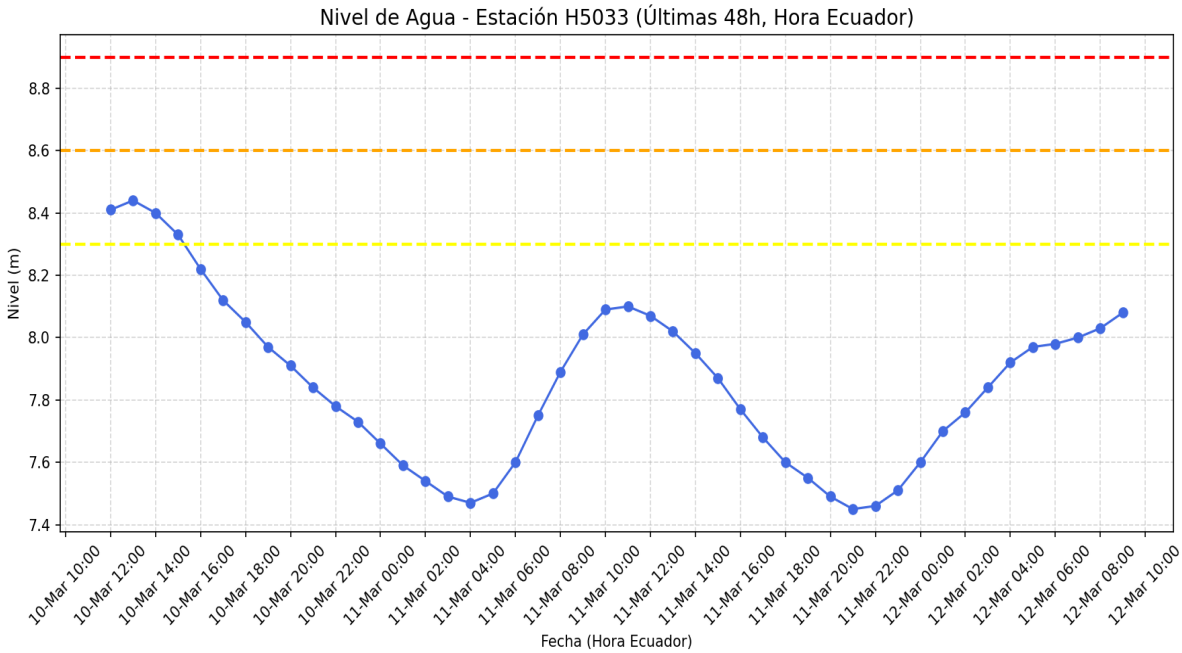

Análisis para la estación San Mateo: actualmente, el nivel alcanzado es de 8.08 m

Monitoreo y Predicción de Condiciones Meteorológicas

Registro diario de precipitaciones

Precipitación registrada en Marzo de 2026 (mm)													
Estación	**Día**	**RR**	**Día**	**RR**	**Día**	**RR**	**Estación**	**Día**	**RR**	**Día**	**RR**	**Día**	**RR**
Tachina – Esmeraldas	1	79.2	12		23		Quinindé – Automática	1	11.64	12		23	
	2	2.2	13		24			2	102.0	113		24	
	3	42.2	14		25			3	151.9	314		25	
	4	NIL	15		26			4	4.82	15		26	
	5	NIL	16		27			5	46.3	16		27	
	6	0	17		28			6	10.22	17		28	
	7	NIL	18		29			7	40.79	18		29	
	8	NIL	19		30			8	6.4	19		30	
	9	NIL	20		31			9	1.65	20		31	
	10	NIL	21		32			10	1.06	21		32	
	11	NIL	22		33			11	3.71	22		33	
Acumulado mensual:			**124**				**Acumulado mensual:**			**381**			
Anomalía mensual:			**-3%**										

En la siguiente tabla se muestran los valores diarios y el total acumulado de lluvia registrados en las estaciones meteorológicas de Tachina y Quinindé, ubicadas en la provincia de Esmeraldas, brindando una visión general del patrón pluviométrico en la zona.

Pronóstico de precipitación en las próximas 24 horas - Modelo WRF

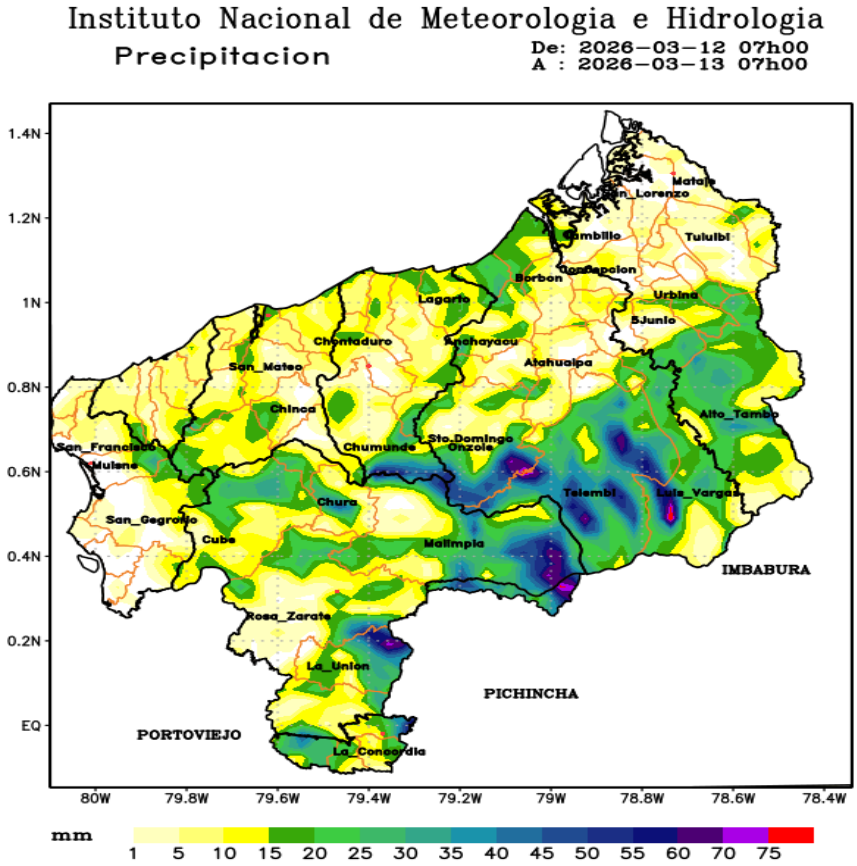

Consideraciones para la interpretación de la imagen WRF: La información visualizada en la imagen de precipitación del modelo WRF se clasifica según los rangos de valores diarios (mm/día) de la siguiente manera:

- **Extremadamente lluvioso:** > 83 mm/día
- **Muy lluvioso:** 43 – 83 mm/día
- **Lluvioso:** 29 – 42 mm/día
- **Moderadamente lluvioso:** 13 – 28 mm/día
- **Poco lluvioso:** < 13 mm/día

Cada valor representa la cantidad estimada de precipitación acumulada en el día, lo que permite identificar rápidamente las zonas con mayor intensidad de lluvia y facilitar la toma de decisiones para alertas hidrometeorológicas.

Elaborado por Dirección de Pronósticos y Alertas Hidrometeorológicas